Manuel d'utilisation de GISWATER 3

Version 3.3

Septembre 2019

Préambule

Le manuel dutilisation de Giswater 3 a pour objectif de répondre aux questions relatives à linstallation et à lutilisation du programme Giswater. Le présent document couvre toutes les informations nécessaires pour les utilisateurs ou intéressés pour savoir comment installer, configurer et utiliser Giswater 3. Le software a été licencié sous une licence GNU-GLP 3 (https ://www.gnu.org/licenses/gpl-3.0). Lindex donne des informations sur la liste des éléments disponibles et est construit en trois bloques principaux qui sont : installation, utilisation et annexes variables.

Remerciements

Ce manuel et le code de Giswater ont été financés par différentes compagnies du domaine de leau de Catalogne qui ont choisi de partager le développement d'un logiciel capable de satisfaire les besoins actuels et futurs dans le monde des systèmes dinformation géographique. Dans cet objectif, le logicie Giswater a été mis au point. Vous avez le manuel entre vos mains.

Nous remercions particulièrement les entreprises du domaine de leau qui ont rendu ce projet possible :

- Aigües de Banyoles, SA
- Aigües de Castellbisbal, SA
- Aigües de Figueres, SA
- Aigües de Vic, SA
- Consorci dAigües de Tarragona
- Proveïments dAigua, SA
- Aigües de Mataró, SA
- Sabemsa
- Aigües de Blanes, SA
- Aigües del Prat, SA

Granollers, 26 septembre 2019

Document licencié sous une licence de Création commune

Table des matières

1 Introduction **1**

1.1 Qu'est-ce que Giswater ? 1

1.2 Quel est l'objectif de ce guide ? 2

1.3 Architecture du système suggéré 3

1.3.1 Serveur de bases de données 3

1.3.2 Serveur web 4

1.3.3 Serveur de distribution 5

1.3.4 Appareils des clients lourds de GIS (QGIS) 6

1.3.5 Appareils des clients légers de GIS (Chrome) 6

2 Installation et mise en marche **7**

2.1 Pré-requis avant l'installation 7

2.2 Téléchargement et configuration de PostgresSQL 8

2.3 Configuration de QGIS 11

2.4 Téléchargement et premiers pas avec le plugin Giswater 13

2.4.1 Installer le plugin dans QGIS 13

2.4.2 Outil généraux de gestion de projet 15

2.5 Création d'un schéma et de projets QGIS 16

2.5.1 Création d'un schéma vide 16

2.5.2 Création d'un nouveau projet d'exemple (échantillon) 22

2.5.3 Création de projets QGIS 23

2.6 Création de projet à partir de zéro 24

1 Introduction

Bienvenue dans le monde de Giswater, le premier software libre avec pour objectif de réaliser une gestion complète du cycle de leau (approvisionnement et assainissement). Ce manuel aidera les utilisateurs à sinitier à lutilisation de Giswater.

1.1 Qu'est-ce que Giswater ?

Giswater est une application libre pensée pour la gestion et lexploitation des éléments de l'infrastructure hydraulique (approvisionnement et assainissement), tant sur base de donné que sur support graphique à travers de tout système d'informations géographiques.

A son tour, Giswater joue aussi un rôle de driver de connexion entre la base de données spéciale et les outils danalyse hydraulique.

A lheure actuelle, Giswater est disponible dans sa version 3 du software qui présente de nettes améliorations comparé à ses versions antérieures, tant sur le plan graphique que dans son utilisation et ses prestations.

Comme représente sur limage , Giswater fait partie dun groupe dapplications qui utilisées conjointement permettent la gestion globale et solide en relation avec les modèles dapprovisionnement deau et de drainage urbain.

Lélément central est la base de données où se trouve toutes les informations et une grande partie de la fonctionnalité de chaque projet Giswater. La base de données pour utiliser Giswater est PostgreSQL qui, avec son extension PostGIS, permet un lien facile avec lapplication QGIS.

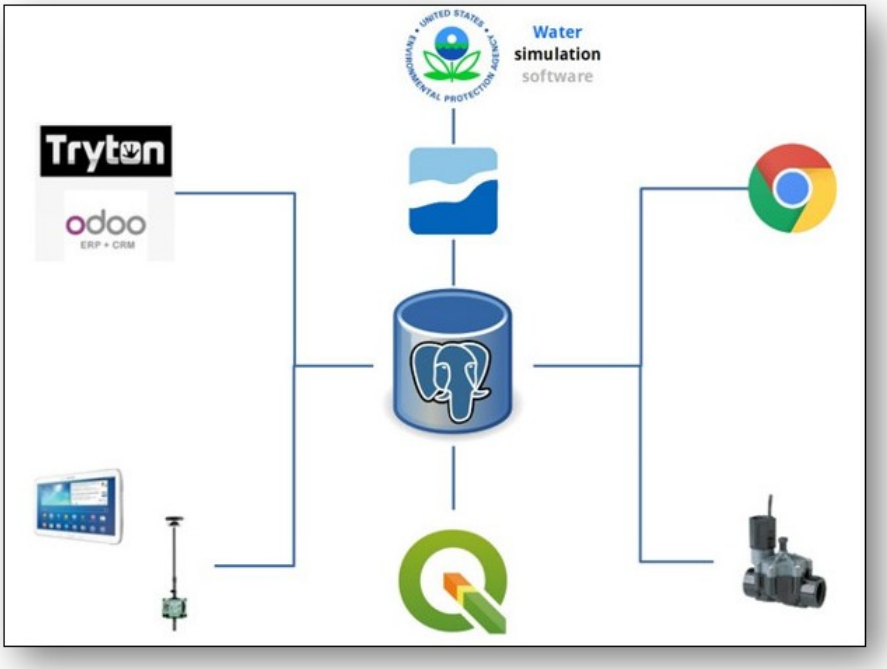

FIGURE 1 – Schéma des applications utilisées par Giswater avec la base de donnée comme élément central.

Ce software de système dinformation géographique est celui sur lequel sest basé le développement du projet Giswater à cause de sa visualisation aisée et pour une plus grande facilité dutilisation pour lutilisateur. QGIS est lié à la base de données grâce à PostGIS pour enregistrer lorganisation spéciale des données et toujours tenir compte des règles, relations et processus qui sont établis dans la base de données.

Le noyau central du projet (la base de données et QGIS) permet aussi une connexion avec SCADA, afin dutiliser en temps réel linformation qui provient directement des éléments physiques du réseau. De cette manière Giswater se présente comme un système de gestion globale et donne la possibilité à ses utilisateurs de toujours travailler avec des données actualisées automatiquement.

A côté de la gestion des données à travers un software SIG, il existe aussi la possibilité de travailler avec les données de Giswater sur le web ou sur appareil mobile. Cette fonctionnalité sajoute lutilisation habituelle sur un deskstop, seulement pour les clients qui le souhaite, et se gère depuis la plate-forme BMAPS.

1.2 Quel est l'objectif de ce guide ?

L'objectif fondamental de ce guide est de proposer à l'utilisateur un document aidant à la réalisation de toute tâche avec Giswater, de l'installation initiale des programmes nécessaires jusqu'aux opérations de gestions

plus complètes.

Les améliorations faites dans la version 3 seront détaillées tout au long du manuel et leurs finalités et utilisations seront expliquées le plus simplement possible.

1.3 Architecture du système suggéré

Le système suggéré est composé de trois machines faisant office de serveurs et pour deux clients. Les clients lourds qui utilisent QGIS comme moteur GIS, et les clients légers, qui utilisent Google Chrome comme moteur GIS.

Comme dans l'architecture du système est présenté sur l'image 2, il est nécessaire d'installer différentes technologies sur des machines distinctes qui sont détaillées ci-dessous.

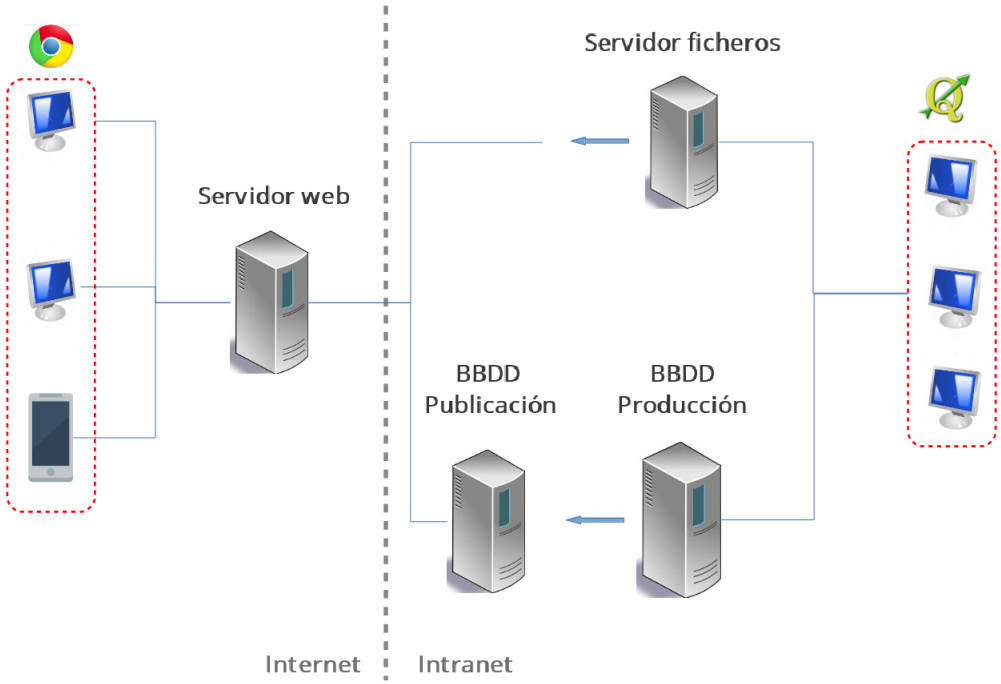

FIGURE 2 – Système d'architecture suggéré avec trois serveurs.

1.3.1 Serveur de bases de données

Premièrement il faut installer la base de donnée du nouveau GIS, dans ce cas-ci il s'agit de PostgreSQL (https ://www.postgres.org) et de l'extension spéciale, PostGIS (https ://www.postgis.net).

Le système opérateur peut être LINUX ou WINDOWS. Pour des raisons de vitesse de traitement, de per-

sonnalisation des performances et fiabilité nous recommandons d'utiliser un appareil (virtuel ou non) avec un système opérateur DEBIAN 9 ou supérieur. Cependant, il n'y a aucun inconvénient à utiliser un appareil Windows avec tout autre système d'opération actuel. Cette décision dépend des préférences du personnel du système d'organisation.

Ce que vous devez garder à lesprit, cest que, selon le nombre dutilisateurs et les enregistrements de l'organisation il est vivement recommandé d'installer la base de données dans un environnement à haute disponibilité. L'objectif est de permettre des consultations simultanées, en particulier celles qui consomment un grand nombre de ressources,puissent être pris en charge sans pénalités.

Étant donné que la base de données fonctionne généralement avec le disque dur pour récupérer ou afficher des informations, il est essentiel que l'appareil dispose d'un disque dur solide (SSD) et d'un contrôleur avec suffisamment de bande passante pour accéder massivement et rapide à l'information. De là, l'architecture de visualisation et la couche de programmation de la gestion dépendra en grande partie du nombre d'utilisateurs et du volume de données à gérer.

1.3.2 Serveur web

Le serveur Web est un autre élément constitutif de l'architecture du système du projet. Ce serveur est probablement celui qui nécessite le moins de ressources puisqu'il sert uniquement à publiez les informations fournies par la base de données. Dans cette partie du système le facteur déterminant n'est plus particulièrement la vitesse ou la capacité du système, mais sa sécurité.

Pour se faire, il est nécessaire dinstaller toutes les technologies nécessaires pour assurer la sécurité, la fiabilité et la performance de l'environnement Web. Une proposition d'un ensemble de technologies pourrait ressembler à ce qui est montré dans l'image suivante.

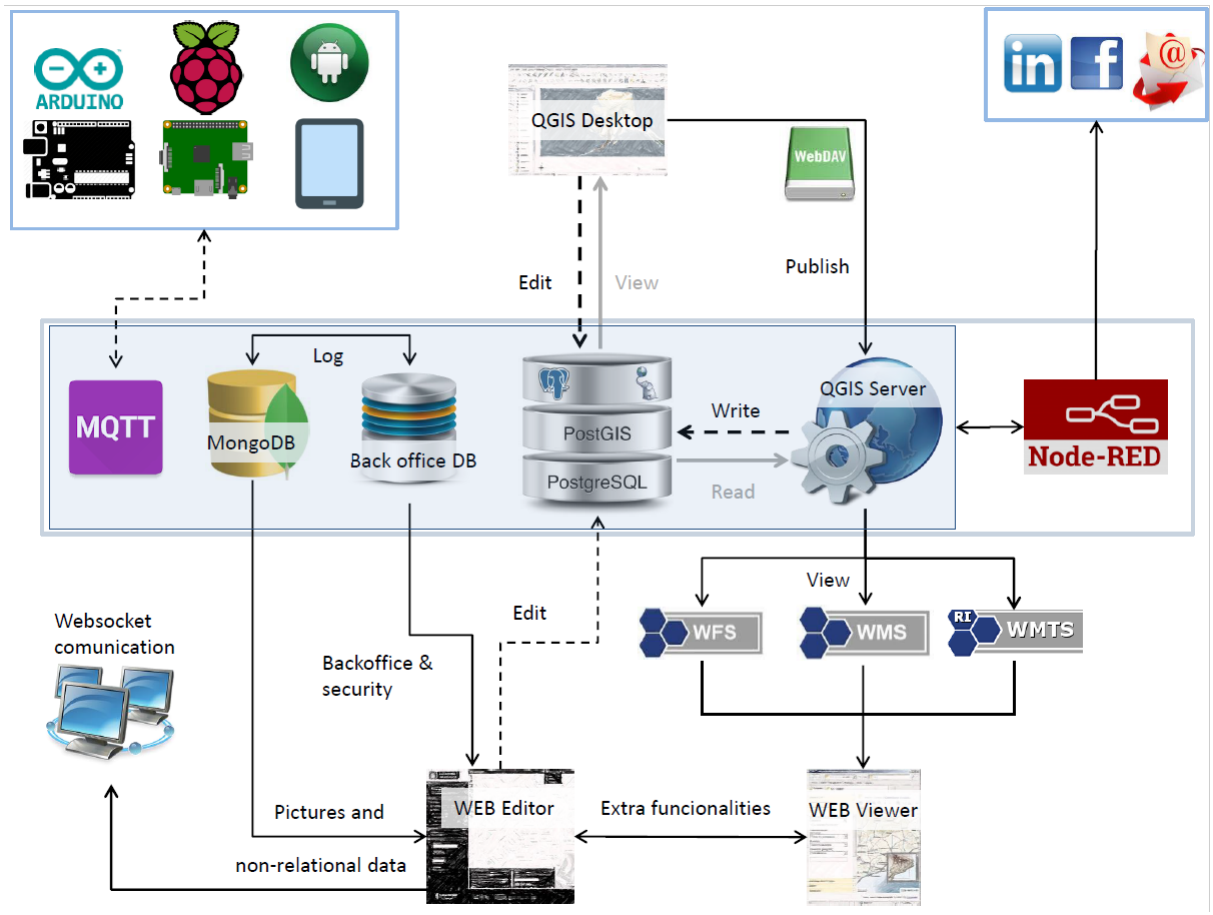

FIGURE 3 – Toutes les technologies qui doivent être installées afin d'utiliser Giswater de la manière la plus fiable.

A l'inverse du serveur précédent, celui-ci doit être obligatoirement en LINUX et distribué en DEBIAN version 9.

1.3.3 Serveur de distribution

Le serveur de fichiers doit être un référentiel centralisé de tous les documents qui doivent être gérer par le système (photographies, dossiers, plans, documentation administrative, etc.) Larchitecture et la technologie de ce serveur dépendront de ce qui est utilisé parl'entreprise et il est recommandé de développer un périphérique de connexion spécifique pour chaque cas.

Les thèmes tels que la publication sur le réseau ou non, le traitement d'un URL ou des chemins de dossiers seront des décisions qui conditionneront larchitecture finale du système et la réutilisation ou non des serveurs de fichiers disponibles pour l'organisation.

Dans tous les cas, pour que le projet Giswater puisse traiter les fichiers qui doivent être utilisés, qui font partie de l'architecture du projet et auxquels tous les utilisateurs doit avoir accès uniquement en mode lecture, sont un dossier de plugins d'entreprise : Giswater plugin Time manager Table manager Un fichier pour partager les projets QGIS de l'entreprise

1.3.4 Appareils des clients lourds de GIS (QGIS)

Comme le montre l'image 3, il existe deux types de machines clientes. Celui avec la plus ancienne configuration requise est celle de QGIS en tant que client de SIG. Dans ce cas, il faudra utiliser au minimum le programme suivants :

— QGIS (https ://www.qgis.org) dernière version avec un LTR stable
— Notepad++ (https ://notepad-plus-plus.org)
— Giswater (https ://www.giswater.org/descarga)

Si lun des modèles hydrauliques compatibles avec Giswater est nécessaire, ces derniers peuvent également être téléchargés à partir du site Web de Giswater :

— EPA SWMM (https ://www.giswater.org/descarga)
— EPA NET (https ://www.giswater.org/descarga)

Pour avoir une meilleure expérience utilisateur avec le logiciel SIG, il est recommandé davoir installé une suite bureautique, ainsi quun lecteur PDF.

1.3.5 Appareils des clients légers de GIS (Chrome)

Il existe également un deuxième type d'apareil client qui sera utilisé en tant que client léger de GIS dans le navigateur Internet, qui remplira les fonctions de WebAPP. Dans ce cas c'est seulement Google Chrome lui-même qui doit être installé.

Il est à noter que le développement nest certifié et validé que par lutilisation du navigateur Google Chrome et que tout autre navigateur, que ce soit Mozilla Firefox, Opera ou Internet Explorer, peut présentent des dysfonctionnements et son utilisation nest donc pas recommandée du tout.

2 Installation et mise en marche

Cette seconde section du manuel d'utilisation détaille toutes les étapes nécessaires pour commencer à travailler avec Giswater, depuis les étapes antérieures à son installation jusqu'à la configuration du programme, en passant par la création de nouveaux projets réel ou servant d'exemple, afin d'essayer le fonctionnement de Giswater.

2.1 Pré-requis avant l'installation

En relation avec la section 1.3, où'il est suggéré l'architecture idéale du système, ici sont détaillés quelques spécificités des trois serveurs qui composent le système.

À côté de serveur de données, la performance dépend beaucoup du nombre d'utilisateurs et du volume de données.

Comme ordre de grandeur et pour commencer avec une des personnes qui éditent les données et entre cinq et huit personnes qui les consultent, avec un volume de données relativement petit respectant le volume de personnel dédié, un appareil de quatre noyaux et un minimum de 32 GB de RAM doit être suffisant.Avec le respect du disque dur, les deux éléments à garder à l'esprit sont la capacité et la vitesse.

Dans le cas d'une organisation plus grande il serait nécessaire d'analyser la technologie des serveurs disponibles et du type de visualisation avec lesquelles ils travaillent pour ajuster aux besoins de la réalité du service et vérifier si le système est suffisant ou si il faut le re-dimentionner.

Si l'appareil est utilisé comme un serveur de PostgresSQL (et la fonction basique de S/O), l'espace du disque occupé par la base de données n'est pas trop élevé. En outre, il est possible de savoir que le disque dur s'utilise pour d'autres fonctions en plus que du stockage des données PostgreSQL. Concrètement cette usage inclus aussi :

- Des fonctions basiques de suport de S/O
- Aide via des fichiers temporels aux processus PostgreSQL
- Stockage de fichiers specifiques de Giswater

Nous recommandons d'assigner initialement environ 100 GB de stockage. Étant donné la vitesse d'accès du disque, ce qui est un sujet particulièrement pertinent, le fait de disposer d'un disque dur solide (SSD) peut favoriser considérablement les prestations vers les utilisateurs finaux avec un contrôle qui garantit l'accès le plus rapide possible aux données.

Du côté du serveur web, moins de prestations sont requises, et pour cela, toujours en considérant la taille de l'entreprise comme mentionné ci-dessus, avec un appareil de deux noyaux (recommandé d'en avoir quatre) et

un minimum de 16 GB de RAM ça devrait être suffisant. Dans tous les cas, cela dépend de la concurrence et de l'utilisation faite du côté du web.

Ce qu'il faut souligner dans ce cas est l'importance du disque pour aller stocker les photos de terrain qui seront réalisées et qui sont gérées par une base de donnée MongoDB. Pour cet effet la dimension du disque, qui ne doit pas être solide, doit être ajusté à l'utilisation pour la capture journalière de photo sur le web.

En ce qui concerne le serveurs de fichiers et respectant le stockage des fichiers spécifiques à Giswater, il est recommandé d'utiliser le même appareil que celui de PostgreSQL pour héberger dans un fichier, seulement en mode lecture, avec un accès partagé du réseau pour les utilisateurs normaux dans lequel ils peuvent trouver un référentiel du *plugin*, les projets de QGIS originaux ainsi que les originaux des instalables.

Dans ce répertoire SIG nous stockerons les modèles des projets QGIS (sous-fichier modèle) et aussi nous configurerons pour que ce soit la route des *plugins* des clients QGIS (sous-fichier plugin) que nous installerons dans tous les appareils du client. Dans le sous-fichier *plugins* nous installerons tous ces compléments qui ont de l'intérêt pour l'organisation.

En respectant les autres type de données (projets QGIS, couche de base cartographique, document adjoints, ect.) nous recommandons de ne pas utiliser le même appareil. La meilleur option est d'utiliser l'unité du réseau partagé avec laquelle on travaille sur les données (pour profiter du système de backups organisé). En configurant tous les utilisateurs client de ce fichier avec les *plugins* avec seulement la permission de lecture, cela garantit que tous les utilisateurs de QGIS disposent des mêmes *plugins* installés et c'est beaucoup plus facile des les actualiser.

Du côté du client les appareils doivent avoir une certaine capacité de traitement (il est recommandé des processeurs i7) avec un minimum de 18 GB de mémoire. Le système opérationnel doit être obligatoirement Windows 7 ou supérieur. Si vous souhaitez effectuer une consommation intensive des ressources avec la génération de geoprocessus de grande intensité, il est recommandé d'utiliser un appareil client avec des prestations plus hautes comme pourrait l'être une multicuore de 16-32 GB de RAM tr un disque dur solide.

2.2 Téléchargement et configuration de PostgresSQL

PostgreSQL est une base de donnée open source avec un énorme potentiel, qui servira pour stocker toutes les données avec lesquelles travailler dans Giswater. Grâce à son extension géospatiale PostGIS, il permet une très bonne relation avec les GIS, particulièrement avec QGIS. Cette extension contient plus de 1000 fonctions geospatiales, ce qui en fait l'un des logiciels GIS les plus puissants existants, bien que PostgreSQL ne soit pas un programme spécifique de GIS.

Il y a différentes versions qui peuvent être téléchargées. Pour travailler avec Giswater il est recommandé de

télécharger toute version postérieur à la 9.5, à partir de laquelle les programmes sont 100% compatibles.

Le téléchargement et l'installation est très simple et peut se faire depuis https ://www.postgresql.org/download. Joint à la base de données s'installe le programme d'administration de la base de données pg Admin (https ://www.pgadmin.org/download/ pour le télécharger), qui servira à gérer la base de données du manière facile et visuelle pour l'utilisateur. Grâce à pgAdmin il sera possible de modifier les tables, les visites et les règles de la base de données, ainsi que consulter toutes l'information et la gérer.

Une fois les deux programmes installés, en ouvrant pgAdmin la première chose à faire est d'ajouter une connexion.

Il faut compléter les champs suivants pour ajouter une nouvelle connexion :

- Name : nonm de la connexion
- Host : ça peut être un hôte local ou une connexion à un autre serveur
- Port : port
- Service : lié à un service configuré dans le fichier pg_service.conf (optionel)
- Username : non de l'utilisateur. Le première utilisateur doit être "postgres"
- Password : le mot de passe qui pour l'utilisateur postgres doit également être "postgres".

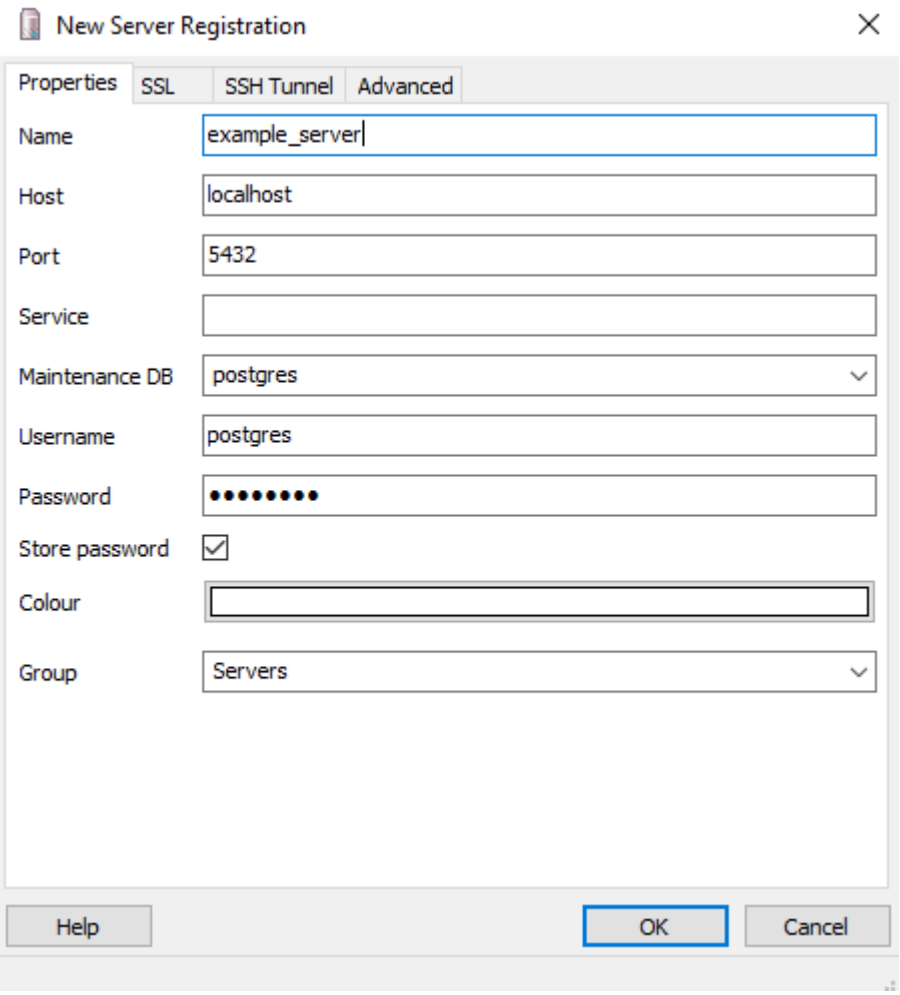

FIGURE 4 – Ajouter une nouvelle connexion à Postgres grâce à pgAdmin.

Une fois que la nouvelle connexion est créé, nous verrons qu'il nous l'a créé automatiquement un premier schéma *public*. Ensuite, il faut ajouter l'extension PostGIS, pour que toutes les fonctionnalités GIS du programme soient disponibles ainsi que l'extension pgRoutine, qui ajoute des fonctionnalités de routage et d'analyse de réseaux à la base de données. pgRouting sera essentiel pour quelques outils de Giswater comme le polygone de coupe et les profils longitudinaux.

En cliquant sur le bouton de commandes SQL nous pourrons écrire notre première *query*.

```
CREATE EXTENSION postgis;
CREATE EXTENSION pgrouting;
```

2.3 Configuration de QGIS

Quqnd vous ouvrez QGIS pour la première fois, une série de paramètres doivent être configurés. Il sont nécessaires pour travailler avec Giswater :

— Créer une connection PostGis à la base de données où les données sont stockées.

— Pour travailler confortablement et de manière confortable avec des donées raster, il est recommandé détendre la mémoire cash de QGIS à 1 GB et 1 an, au travers du menu 'Configuration/ Options/Réseau'.

— Choisir d'ouvrir le formulaire si une entité seule est sélectionné.

— Configurez deux variables dans les propriétés du projet (Projet/ Propriétés du projet/ Variables). Pour ajouter une nouvelle variable à celles qui apparaissent par défaut, il y a un bouton :

1. project_type ⇒ ud/ws (dépend du projet).
2. expl_id ⇒ valeur d'exploitation par défaut qui sera montrée après l'ouverture du projet.

Comment configurer une nouvelle connection entre QGIS et PostGIS ?

1. Cliquez sur l'icône **Ajouter une couche Postgis**

2. Cliquez sur **Nouveau** et le formulaire intruduit les paramètre de connection.

Nom de la connection

Server où sont stockées les données

Port sur lequel Postgres est installé

Nom de la base de données

Nom de l'utilisateur Postgres

Mot de passe de l'utilisateur Postgres

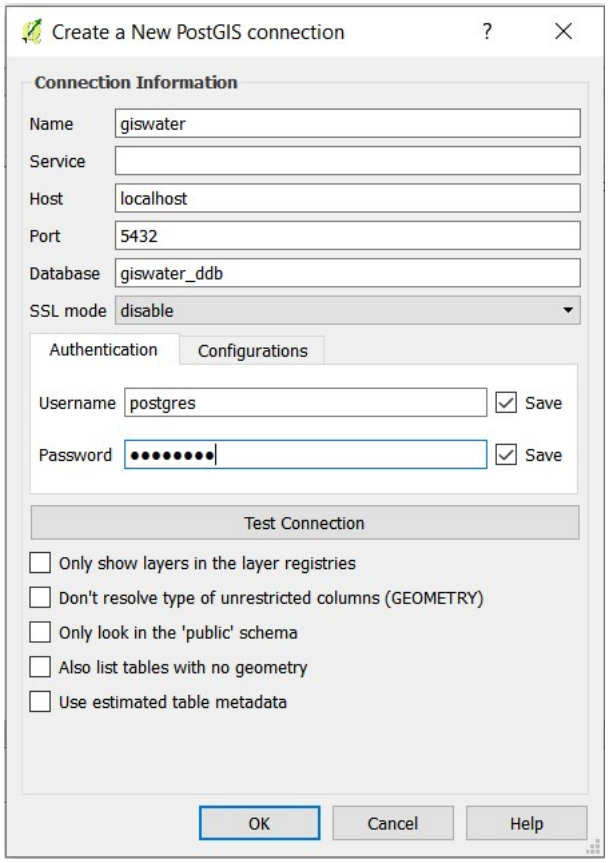

FIGURE 5 – Formulaire QGIS de connection avec PostGis

3. Une fois que les pqrqmètres sont complètés, cliauez sur**Tester la connection** : Si tout est correct, le message suivant va apparaître :

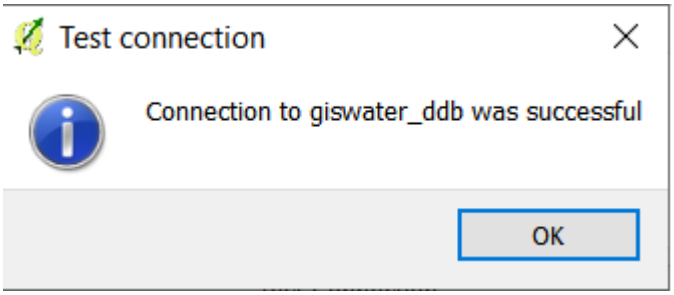

4. Cliquez **OK** : À ce moment là les informations de la connection seront sauvées avec le nom dans la liste de connection. Pour utiliser le plugin **Giswater**, il est nécessaire dávoir créer une connection à une base de données aui sera utilisée pour travailler. Cela a besoin d´être créerune fois pour chaque QGIS installé. De multiples connections à différentes bases de données est possible, bien aaue dans ce cas il est recommandé de travailler avec précaution pour éviter le mélange de données entre base de données. Une fois connectés, nous pouvons visualiser les tables (avec et sans géométrie) que contient

la bases de données correspondantes et, si nécessaire, les ajouter qu projet.

2.4 Téléchargement et premiers pas avec le plugin Giswater

Dans la version précédents, Giswater était composé d'une application, ce qui faisait office de conducteur pour la configuration, la création et la gestion des différents projets de la base de donnée, et le plugin basé sur QGIS pour l'exploitation des éléments du réseau. En commençant de la version 3.2, il sera seulement nécessaire d'installer le plugin dans QGIS pour développer les fonctions mentionnée. Pour télécharger le plugin, le lien URL du dépôt est nécessaire : https ://download.giswater.org/plugin/3.2/giswater.xml

Il peut être trouvé sur le site web de Giswater (https ://www.giswater.org/downloads/), de là il est aussi possible d'accéder aux versions antérieures du plugin. Dans la section de téléchargement, il est aussi possible d'accéder à l'information sur le produit, les bénéfices d'utiliser des programmes libres, la communauté d'experts qui développe Giswater et pour obtenir le matériel et les tutoriels relatifs au plugin.

2.4.1 Installer le plugin dans QGIS

Afin d'installer et de connecter le plugin Giswater dans QGIS, il est nécessaire de configurer un nouveau référentiel, ce aui permettra de voir le plugin Giswater dans la liste des plugins. Il faut suivre les étapes suivantes :

1. Ouvrir QGIS et accéder au référentiel de plugins.
2. Accéder à l'onglet de configuration et ajouter un nouveau référentiel.

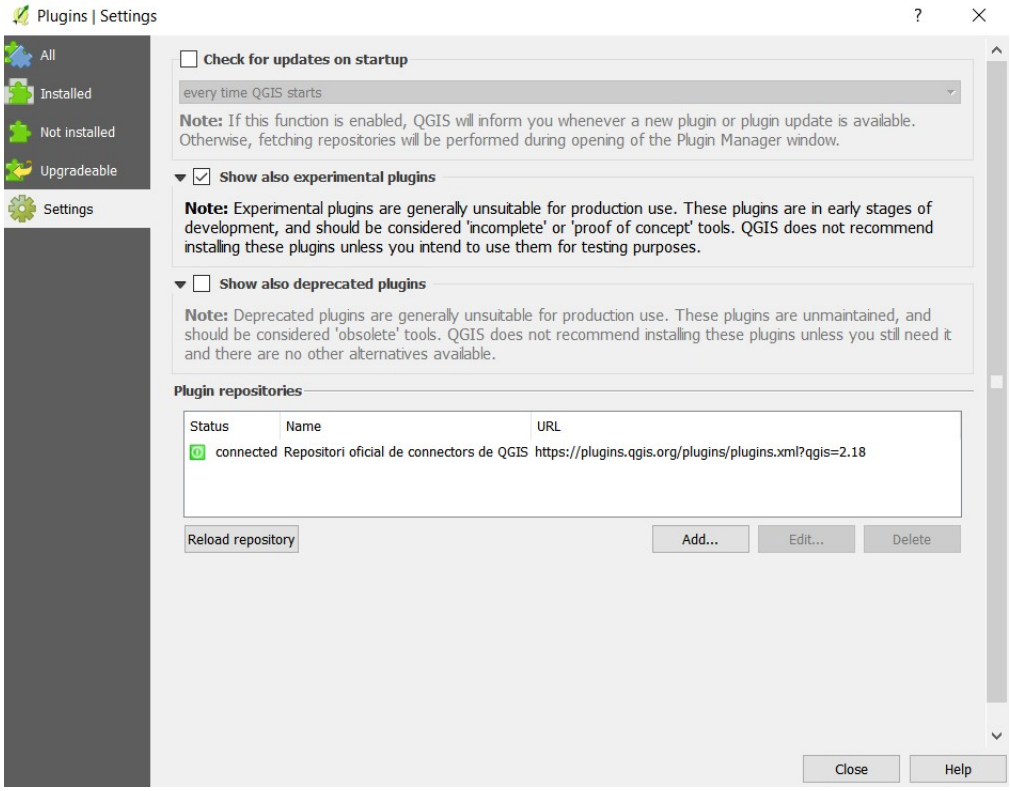

FIGURE 6 – Afin d'installer le plugin, il est nécessaire de trouver l'onglet Configuration

3. Introduire le nom et identifier le référentiel et l'URL.

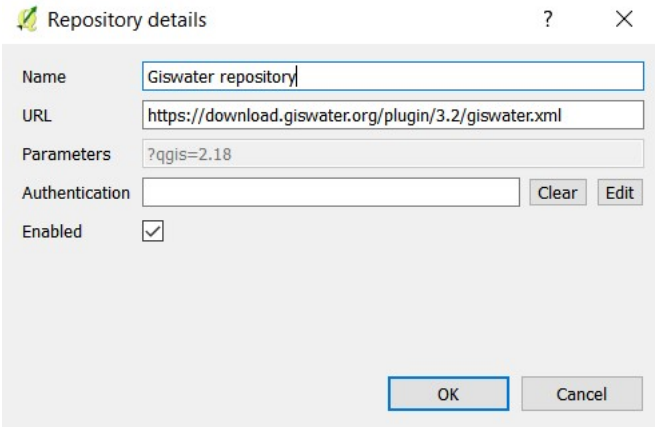

4. Trouver et installer le plugin Giswater depuis le formulaire de l'onglet "tous"·

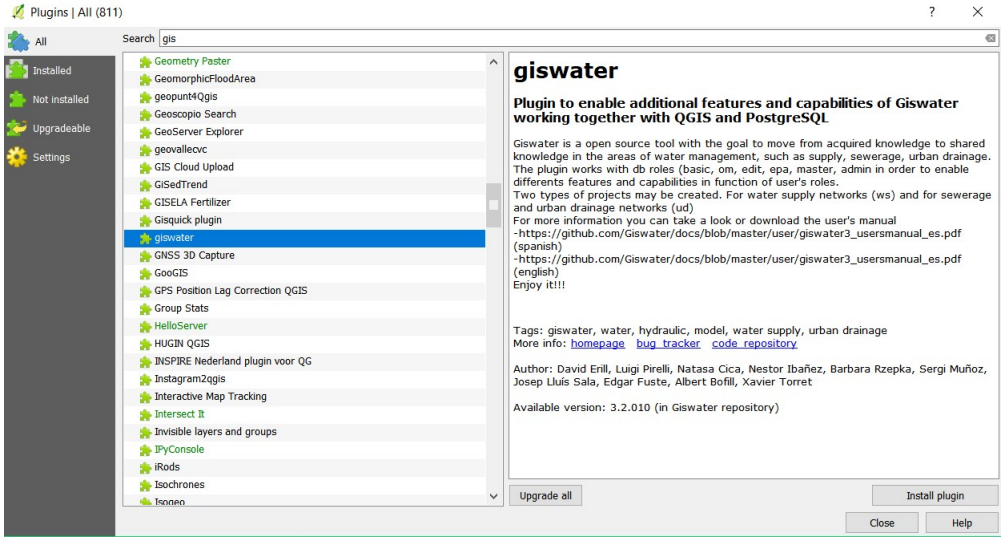

FIGURE 7 – Il est toujours possible de cocher la version actuelle du plugin et la nouvelle verison disponible

Attention : Si nous souhaitons mettre à jour le plugin à la verison la plus récente, cela peut être fait, mais cela peut avoir des implications que nous verrons plus tard. Si après avoir installer le plugin et configurer la connection de la base de donnée, si il n'apparaît pas directement dans la bare d'outil, aller dans le menu "Vue / barre d'outil" et ajouter la. Si vous avez plus d'un projet QGIS ouvert, le comportement duplugin peut présenter des instabilités, il est donc recommandé de ne pas utiliser le plugin avec plus d'un projet QGIS ouvert.

2.4.2 Outil généraux de gestion de projet

C'est un outil important pour commencer à travailler avec Giswater. Contrairement aux autres boutons que le plugin contient, il se trouve dans la bare d'outil générale à côté des autres boutons de différents plugins installés spécifique à QGIS.

La plupart des fonctionnalités de cet outil vont seulement être exécutée si nous ouvrons QGIS sans aucun projet Giswater (nous considérons par un projet Giswater un projet qui a au minimum la représentation des couches de noeuds, arcs, connecs et la version du schéma de la base de donnée). Une fois dans un projet Giswater, l'outil sert seulement à montrer la version du plugin, le cadre de travail, la version de postgres et de postgis.

Dans le cas de l'initialisation et des premières étapes avec le plugin, nous devons savoir comment utiliser cet outil pour réaliser toutes ces fonctions :

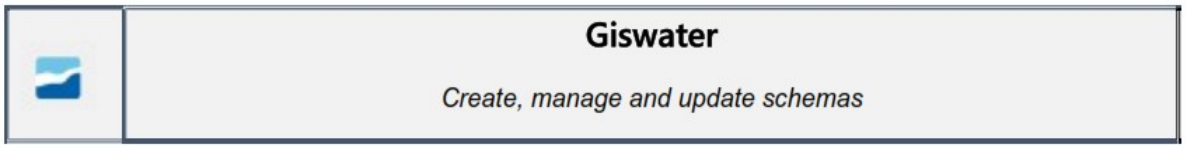

— Générer un nouveau cadre de travail directement dans la base de donnée
— Montrer les cadres existants
— Actualiser et éditer les nouveaux schémas
— Montrer les informations sur le schéma sélectionné

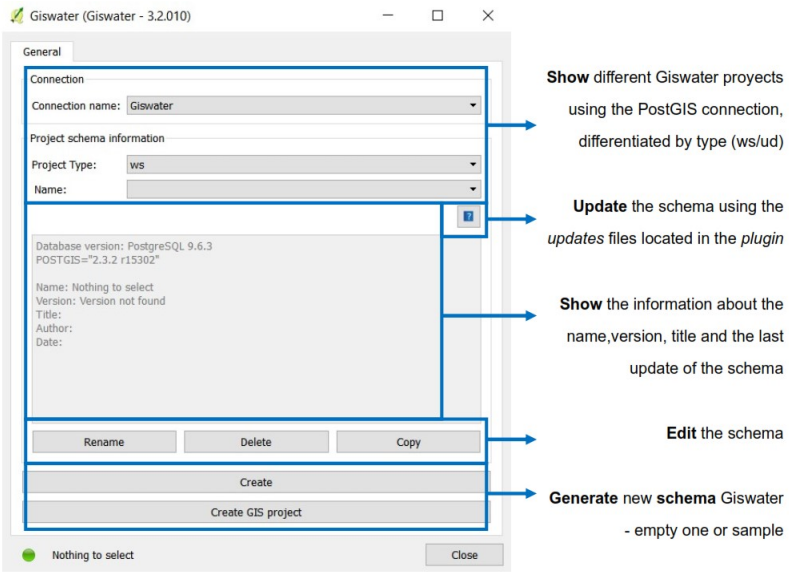

FIGURE 8 – Menu principal de l'outil Giswater

2.5 Création d'un schéma et de projets QGIS

2.5.1 Création d'un schéma vide

En utilisant l'outil général de getsion de projet, qui a déjà été présenté dans la section 2.4.2, nous allons créer un modèle basique du schéma de travail dans la base de donnée, ce qui peut être ouvert et éditer comme un projet QGIS. Un shéma vide ne veut pas dire qu'il n'y a pas de donnée dans les tables. Les valeurs commune et du système nécessaires pour le fonctionnement correcte de l'outil sont présentes, cependant il n'y a pas de réseau d'information.

La première chose qu'il faut garder à l'esprit es que cette outil, dans la première liste déroulante appelée Nom de la connexion, s'affiche toutes les connexions PostGIS créées dans notre QGIS. Dans la section 2.3 de ce manuel, une connection avec le nom Giswater était créer, donc cette connection apparaît comme disponible

dans l'outil (Figure...). Il est important de prendre en compte les paramètres donné à la connection comme maintenant ils vont être utilisé et créer le shcéma.

Connaissant quelle base de donnée appelle la connection, cliquer **Créer** afin d'ouvrir le formulaire de configuration du nouveau schéma.

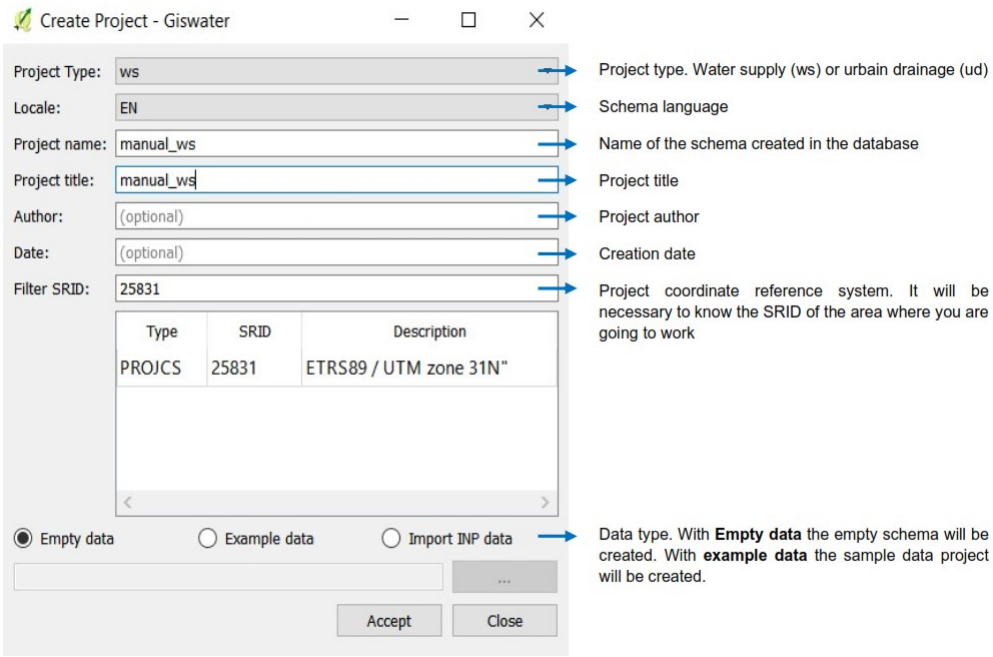

FIGURE 9 – Formulaire de création de nouveau schéma. En sélectionnant **données vides** nous allons créer un schéma vide

Après avoir cliquer sur Acepter, le schéma va être créer et le programme va idiquer ce statut :

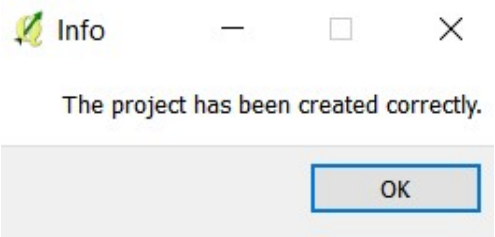

Il est aussi possible de voir le résultat dans la base de donnée, en utilisant pgAdmin. Le schéma *manual_ws* devrait apparaître dans la base de donnée. Il devrait y avoir des tables, des séquences, des fonctions, des déclencheurs et des vues aui sont des modèles du projet d'approvisionnement en eau de Giswater.

Configuration basique d'un projet modèle Il existe de nombreux types de tableaux parmis tous ceux créés dans la section précédente. Il y en a qui sont déjà rempli par défaut, d'autres qui seront remplis lorsque des éléments du réseau seront créés et il y a des tableaux personnalisables par les utilisateurs, en fonction de leurs besoins et de ceux de leur réseau. Les tableaux de base qui correspondent aux principaux éléments génériques de tout projet Giswater sont d'une grande importance et doivent être pris en compte pour expliquer cette section. Ce sont les suivants :

— Arc
— Node
— Connec
— Gully (seulement pour UD)

Ces quatre tableaux sont vides et ne seront remplis que lorsque le projet aura des éléments géospatiaux du type correspondant. L'important est qu'ils ont de nombreuses restrictions et relations avec d'autres tableaux qui doivent être remplis.

Voici les tableaux qui, depuis le début, doivent être remplis par l'utilisateur pour que Giswater fonctionne correctement.

1. Création d'éléments de réseau nouveaux et personnalisés

   cat_feature
   node_type
   arc_type
   connec_type
   gully_type (only for UD)

   Ces tableaux sont utilisés comme catalogue intermédiaire pour tous les éléments des différents types. Chaque élément créé doit nécessairement faire partie d'un type d'élément (feature_type), qui peut être nud, arc, connec ou gully, et en plus d'un autre type dans chacun des ci-dessus, spécifié dans la table sys_feature_type (non modifiable par les utilisateurs). Il y a 24 enregistrements pour les projets d'approvisionnement en eau (ws) et 17 pour l'assainissement (ud).

Chaque utilisateur peut personnaliser la table cat_feature avec des éléments spécifiques nécessaires à son réseau, à condition qu'ils soient liés à l'un des champs sys_feature_type (par exemple, TANK ou FONTAINE) et l'un des feature_type existants (par exemple, NODE ou CONNEC).

Les tableaux suivants qui doivent être remplis sont ceux des types d'éléments liés à un seul feature_type (node_type, arc_type, connec_type et gully_type). L'ID de la table cat_feature doit correspondre à l'ID des tables * _type, qui, bien entendu, n'auront que des éléments de leur type spécifique. Les tables * _type se connectent aux tables de gestion individuelles de chaque type d'élément, aussi bien que celles qui sont en action sur les modèles hydrauliques (inp).

Pour terminer la hiérarchie des tables qui déterminent les éléments existants, les tables de catalogue doivent être rempli en reliant chaque nouvel élément, avec un nom au goût de l'utilisateur, avec un ny des types spécifiés dans les tableaux de hiérarchie supérieure (voir section 4.2.1.1

2. Domaines de valeur personnalisés

   man_type_category

   man_type_fluid

   man_type_function

   man_type_location

   Dans ces tableaux, les informations spécifiques sur le type de catégorie, de fluide, de fonction ou d'emplacement liés aux les différents types d'éléments de base (arc, connexion de nud, gully) sont définis. Chacune des tables ont les champs suivants :

id	serial	Automatic id (primary key)
*_type	varchar (50)	Field to put in the information that will be used in arc/node/connec/gully table
feature_type	varchar (30)	Element type to which the value is assigned
featurecat_id	varchar (30)	Allows to detail to which kind of element is assigned the value
observ	varchar (150)	Field for additional information

*category/fluid/function/location

Pour donner un exemple d'utilisation de ces tableaux, nous pourrions définir un catalogue de domaine de valeurs personnalisées pour un réservoir en plus de ce qui lui correspondrait par nud. Ces champs sont gérés par la base de données via des clés étrangères pour garantir la cohérence et l'unicité des informations. La clé étrangère a des caractéristiques spéciales pour régir ce système de valeurs différentes selon la table source. L'une des propriétés les plus importantes est la duplicité de la clé étrangère. Cela signifie que, pour donner un exemple pour la table des nuds, et en ce qui concerne le type de fluide, la double clé est gérée de sorte que seules les valeurs de fluid_type dans la table man_fluid_type qui remplissent la condition d'avoir le champ feature_type = 'NODE' seront disponibles dans le champ node.fluid_type. La double clé étrangère garantit la cohérence des informations à tout moment, évi-

tant les insertions non conformes à ce critère et généralisant les changements en cas de renouvellement ou d'élimination des domaines de valeur.

3. Vérification de valeurs

   value_verified

   Ce tableau permet de personnaliser le champ vérifié présent dans tous les tableaux des éléments de base. Chaque utilisateur, en fonction de ses besoins, peut ajouter des valeurs de vérification afin d'améliorer la précision de ses données. Voici quelques exemples de valeurs de vérification : à réviser, à vérifier, en attente de confirmation, etc.

4. Configuration de tables intégrées dans des formulaires

   config_client_forms

   Ce tableau est utilisé pour personnaliser la visibilité de tous les tableaux intégrés dans les formulaires et vise à personnaliser les champs visibles, leur largeur et quel est l'alias de la colonne.

   La relation doit être configurée et son apparence est détaillée dans le tableau ci-joint :

project_type	location_type	table
utils	basic toolbar	v_ui_workcat_x_feature_end
utils	basic toolbar	v_ui_workcat_x_feature
utils	om toolbar	v_ui_om_visit
utils	om toolbar	om_psector
utils	edit toolbar	Doc
utils	edit toolbar	element
utils	epa toolbar	v_ui_rpt_cat_result
utils	plan toolbar	plan_psector
utils	plan toolbar	v_ui_om_result_cat
utils	node form	v_ui_scada_x_node
utils	node form	v_ui_scada_x_node_values
utils	node form	v_ui_element_x_node
utils	node form	v_ui_om_visit_x_node
utils	node form	v_ui_doc_x_node
utils	arc form	v_ui_element_x_arc
utils	arc form	v_ui_om_visit_x_arc
utils	arc form	v_ui_doc_x_arc
utils	connec form	v_ui_doc_x_connec
utils	connec form	v_ui_element_x_connec
utils	connec form	v_ui_om_visit_x_connec
utils	connec form	v_rtc_hydrometer_x_connec
ws	om toolbar	v_ui_anl_mincut_result_cat
ws	node form	v_ui_node_x_relations
ws	connec form	v_ui_mincut_hydrometer
ud	node form	v_ui_node_x_connection_downstream
ud	node form	v_ui_node_x_connection_upstream
ud	gully form	v_ui_doc_x_gully
ud	gully form	v_ui_om_visit_x_gully
ud	gully form	v_ui_element_x_gully

D'un autre côté, la table de configuration a les colonnes listées : id serial, location_type, project_type, table_id, column_id, column_index, status, width, alias, dev1_status, dev2_status, dev3_status, dev_alias, où pour la configuration du client QGIS il suffit d'agir sur les champs :

status : vrai/faux si il doit être montré ou non dans le formulaire

alias : le nom de la colonne montrée

width : la largeur du champ montré

Les champs dev1_status, dev2_status, dev3_status and dev_alias sont créés pour les utilisateur avec des appareils mobiles.

5. Création d'attributs personnalisés **man_addfields_parameter**

   Cette table, comme son nom l'indique, est destinée à ajouter des champs à tout élément de projet non créé par défaut dans Giswater. Cela permet aux utilisateurs de personnaliser les champs selon ses exi-

gences. De cette façon, à tout moment, s'il est nécessaire de lier tout type d'informations à un élément, il est possible de le faire via ce tableau. Il existe trois autres tableaux liés à man_addfields_parametre.

— man_addfields_cat_datatype : catalogue des types de données(entier, texte, boolean)
— man_addfields_cat_widgettype : catalogue des types de widget types dprésentés dans le formulaire (QCheckBox,QComboBox, QTextEdit ...)
— man_addfields_value : table où les valeurs sont stockées pour chaque type de paramètre ajoutés par l'utilisateur.

Les informations contenues dans les champs de ces tables ne peuvent pas être affichées dans la table attributaire de l'élément, mais il sera vu dans le fomulaire correspondant et dans les tables addfields.

6. Configuration des fonctionnalités de visite, d'inspection et de planification.

   om_visit_parameter

   La table om_visit_parameter permet d'ajouter des champs pour chaque type d'inspection qui peut être fait dans le réseau d'eau. Tout type de visite peut être défini (par exemple, inspection ou réhabilitation) pour répondre aux besoins de l'utilisateur. Cependant, la visite doit également être liée à un type d'élément existant.

   plan_psector

   Il est nécessaire d'insérer au moins un secteur de planification avant de commencer à travailler. Cette zone fonctionnera comme secteur par défaut pour les nouveaux éléments panifiés.

2.5.2 Création d'un nouveau projet d'exemple (échantillon)

Pour faciliter le premier pas avec Giswater et avoir un modèle de données complet qui sert de source de référence, Giswater a incorporé deux exemples de schémas, à la fois pour le drainage urbain 'ud_sample' et pour l'approvisionnement en eau.net wo rks 'ws_sample'.

Avoir un modèle de données complet, en plus de servir comme source de requête pour voir comment les données sont structurées dans chacune des tables, permettra de commencer par un environnement et de s'exercer avec toutes les fonctionnalités que contient le plugin de Giswater.

Afin de créer l'échantillon, répétez les étapes précédentes de création d'un schéma vide, expliquées dans la section 2.5.1. Cette fois, au lieu de *Données vides* sélectionnez.

L'exemple de projet de Giswater sera créé automatiquement avec toutes les informations et données échantillon qui permettent de voir toutes les fonctionnalités du plugin. En utilisant la version 3.2 du plugin, il est possible de donner un nom à l'exemple de schéma, pas comme dans les anciennes versions, où le nom était déterminé par défaut.

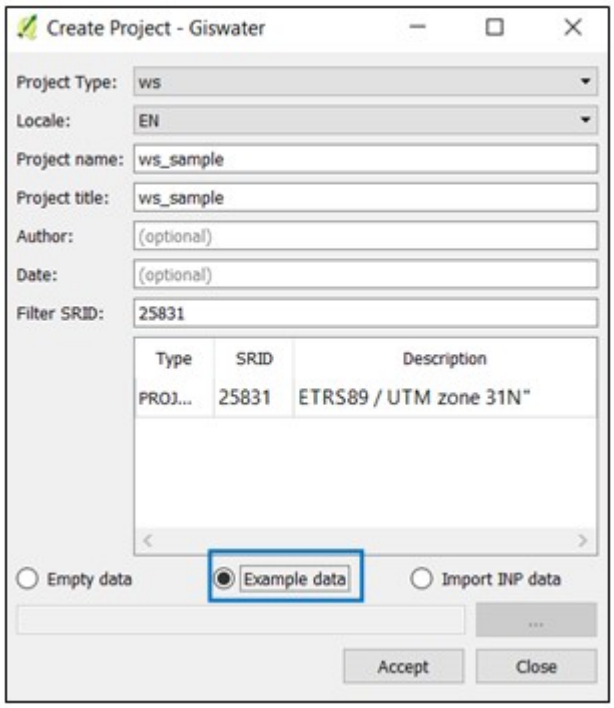

FIGURE 10 – Formulaire de création d'un nouveau schéma. En sélectionnant **Données exemples** nous allons créer un schéma échantillon.

2.5.3 Création de projets QGIS

L'outil général de gestion de projet, en plus de créer des schémas avec ou sans données, donne la possibilité pour générer automatiquement des projets QGIS. Ils sont conçus pour fonctionner avec les tables de la base de données et visualiser les données avec une symbologie qui permet d'utiliser les données du projet aussi facilement que possible. Pour créer un nouveau projet QGIS, cliquez sur le bouton **Créer un projet SIG** situé dans la partie inférieur du formulaire.

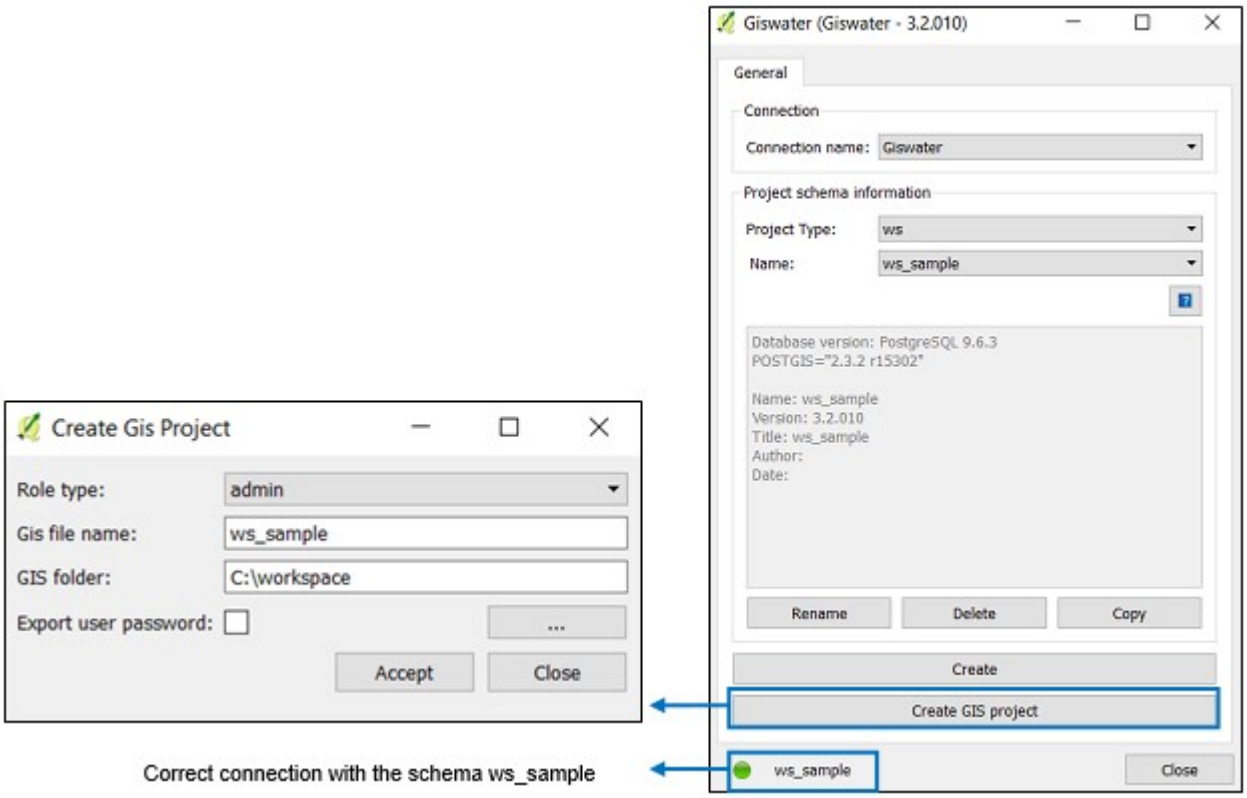

FIGURE 11 – Créer un nouveau formulaire de schéma. Avec le bouton **Créer un projet GIS** il est possible de créer un projet QGIS de Giswater

Enfin, créez un nouveau projet QGIS pour visualiser et commencer à travailler avec les exemples de données. En cliquant sur le bouton OK, l'exemple de projet QGIS sera créé, ce qui permettra de commencer à travailler avec les exemples de données. Le projet généré est spécifiquement créé pour fonctionner avec les tables de la base de données, ainsi que conçu avec une symbologie qui permet de visualiser les données du projet de la manière la plus confortable possible.

2.6 Création de projet à partir de zéro

Si ce que nous voulons est de démarrer notre projet à partir de zéro, avec les données réelles de notre réseau, nous devons comptez les couches vitales pour qu'au moins le plugin Giswater soit activé une fois que nous sommes à l'intérieur du projet QGIS. Les couches essentielles requises par le plugin sont celles qui appellent les vues :

— **v_edit_arc** vue de tous les éléments de la table arc.

— **v_edit_node** vue de tous les éléments de la table node.

— **v_edit_connec** vue de tous les éléments de la table connec.

— **v_edit_gully** (seulement UD) vue de tous les éléments de la table gully.

De plus, les tableaux listés doivent être chargés :

— **version** table qui stocke les informations sur les différentes versions des programmes (G iswater y PostgreSQL), la date de création du schéma, la langue par défaut ou EPSG.

— **exploitation** valeur d'exploitation à laquelle appartient le réseau. Il devrait être défini au moins une exploitation pour que le plugin s'active. Il est également nécessaire de filtrer les données projet utilisant l'expl_id.

Une fois l'information se trouve dans les tables de la base de données créée manual_ud), vous pouvez créer un projet QGIS et visualiser enfin l'information dans un logiciel spécifique de systèmes d'information géographique. Dans les préférences du projet de Giswater et avec la connexion ouverte à manual_ud, cliquez directement sur le bouton 'Créer un projet SIG'. Cela ouvrira le menu indiqué ci-dessous où les paramètres suivants sont configuré : emplacement où le fichier QGIS sera enregistré, nom du fichier, type de projet (choisissez entre UD et WS) et le schéma de base de données avec lequel il sera lié. Une fois tous les paramètres définis, le projet sera créé. Le projet QGIS relie toutes les tables et vues du modèle de données créé dans la section 2.3.4 avec les informations renseignées au début de cette section.